# BADAN PERTANAHAN NASIONAL

# BUKU TANAH

BHUMIBH[illegible]HIGUNA

DAFTAR ISIAN 208

No. 1119 / II / 96

DAFTAR ISIAN 307

No. 969 / II / 96

KANTOR PERTANAHAN

KABUPATEN [illegible]

[illegible]





[illegible] DAN PENCATATAN LAINNYA

| [illegible] | [illegible] | Tanda tangan Kepala Kantor dan Cap Kantor |
|---|---|---|
| | [illegible] | |

**PEMERINTAH KOTA TASIKMALAYA**

Tasikmalaya,

**KEPALA KANTOR PERTANAHAN**

**KOTA TASIKMALAYA**

**Ir. [illegible]**

**NIP. [illegible]**

BHUMIBHAKTI ADHIGUNA

**PERBANDINGAN 1 : ....500....**

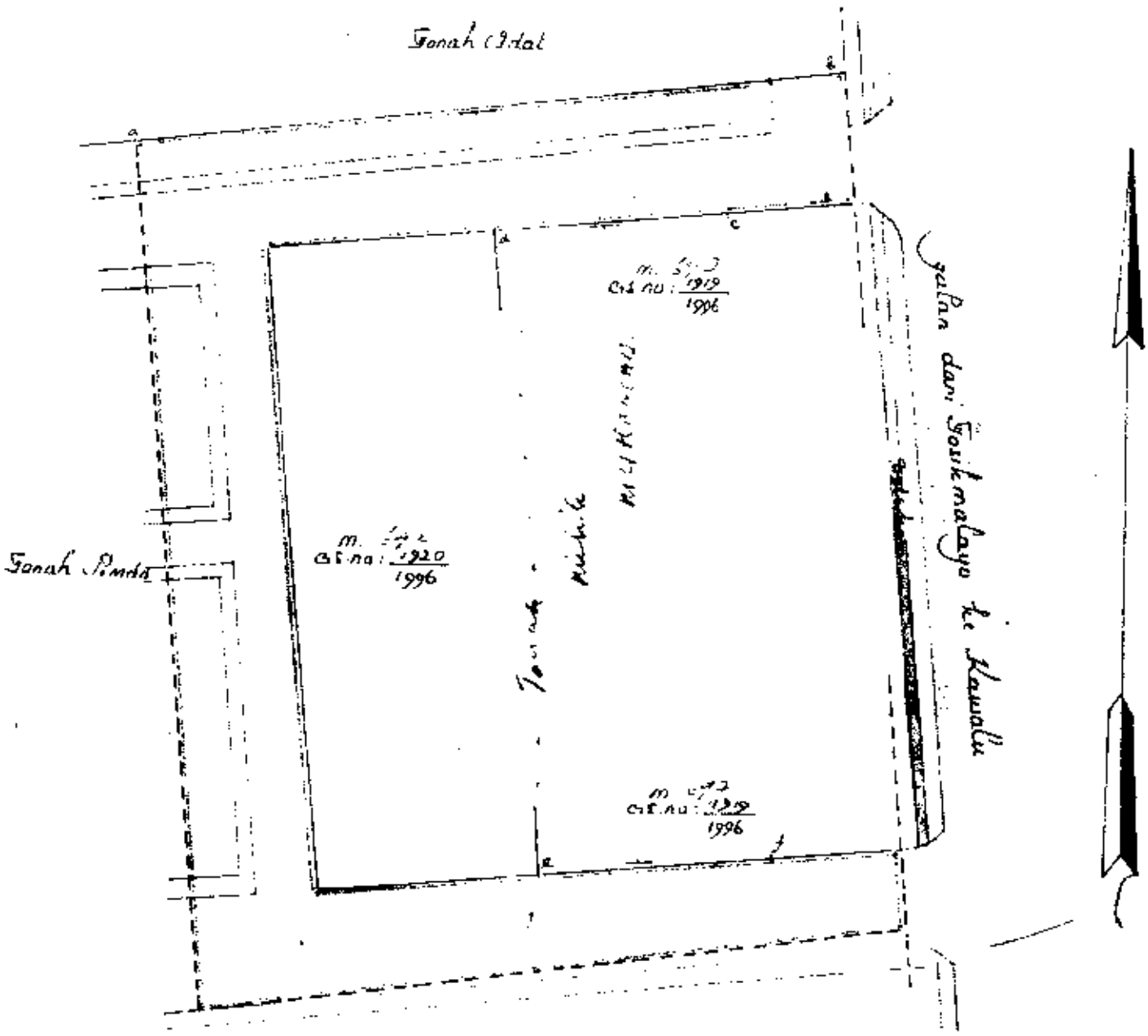


**PENJELASAN : .....** batas tanah ini

10.18.72.06.4.00019

DAFTAR ISIAN 201

Nomor hak : [illegible]

# SURAT UKUR
# GAMBAR SITUASI

Nomor : 1921 /19 96.

SEBIDANG TANAH TERLETAK DALAM

Propinsi : JAWA BARAT

Kabupaten/Kotamadya : TASIKMALAYA

Kecamatan : CIHIDEUNG

Desa/Kelurahan : TUGUJAYA

Peta : TASIKMALAYA

Lembar : [illegible] Nomor Pendaftaran : [illegible]

Blok : [illegible]

Keadaan Tanah : [illegible]

Tanah-tanah batas : Tembok a-b berdiri didalam

Tembok c-d dan e-f berdiri diluar.

Luas : 1585 M2 ( Seribu lima ratus delapan puluh lima meter persegi )

Penunjukan dan penetapan batas : Batas-batas ditunjukkan oleh : Muhamad.

BHUMIBHAKTI ADHIGUNA

Hal lain-lain : Tanah ini asalnya diuraikan dalam Gambar Situasi Tgl.5-9-1983

No : 1651 / 1983.

Daftar Isian 302 tgl. 14 - 5 - 1996 No. 931

Daftar Isian 307 tgl. 14 - 5 - 1996 No. 1168

UNTUK SERTIPIKAT

Tan[illegible]

Tgl. 3 - 6 - 19 96

Kepala Kantor Pertanahan

[illegible]

[illegible]

010 [illegible] 728

[illegible], Tgl. 14 - 5 - 19 96

Kepala Seksi Pengukuran dan Pendaftaran Tanah

Kantor Pertanahan

Kabupaten/Kotamadya [illegible]

ttd

[illegible]

[illegible]

BHUMIBHAKTI ADHIGUNA

Pemisahan

Penggabungan Nomor [illegible] /19[illegible] Nomor hak

Pengganti

| Gambar situasi | | | | |
|---|---|---|---|---|
| Nomor | Luas | Nomor hak | Sisa luas | |
| | | | | |

/19[illegible] Nomor hak